LOKALIA.

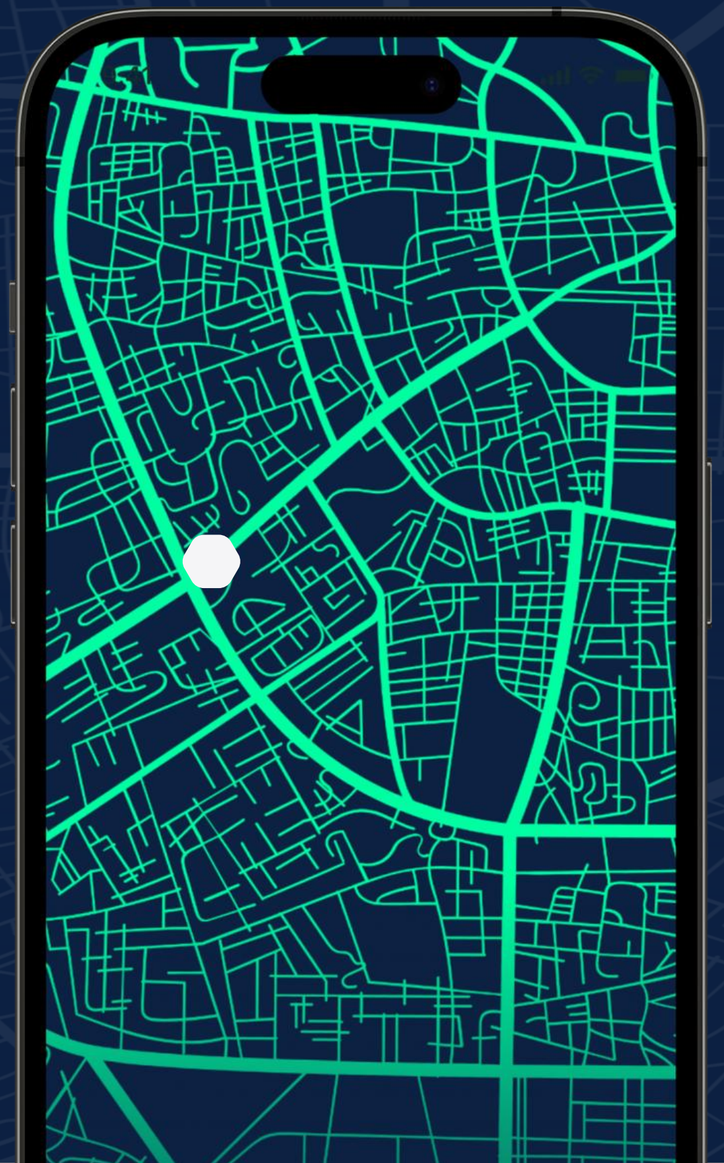

Jesús Debén Rodríguez

DA2D1E

EL RETO 1+1: ORIGEN

+

EL PROBLEMA DEL CAOS

El rastro es un laberinto:

1. Dificultad para encontrar puestos
2. Falta de información diaria
3. Experiencia desorganizada

LA SOLUCIÓN: LOKALIA

La App que transforma el caos en orden.

Funcionalidades principales:

1. Mapa en Tiempo Real y GPS
2. Inventario Digital (por búsqueda)
3. Actualización Diaria de puestos

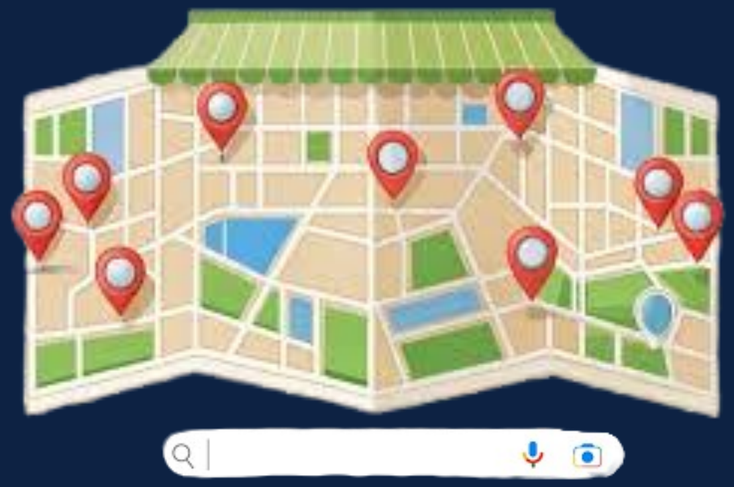

¿A QUIEN SERVIMOS?

1. Turistas: descubren El Rastro sin perderse, encuentran recuerdos de Madrid de forma eficiente
2. Coleccionistas/Expertos: buscan artículos específicos usando filtros avanzados
3. Vendedores del Rastro: ganan visibilidad digital y un canal de comunicación con sus clientes
4. Visitantes locales: planifican su ruta y encuentran rápidamente zonas de ocio y restauración cercanas





TÉCNICA SCAMPER:

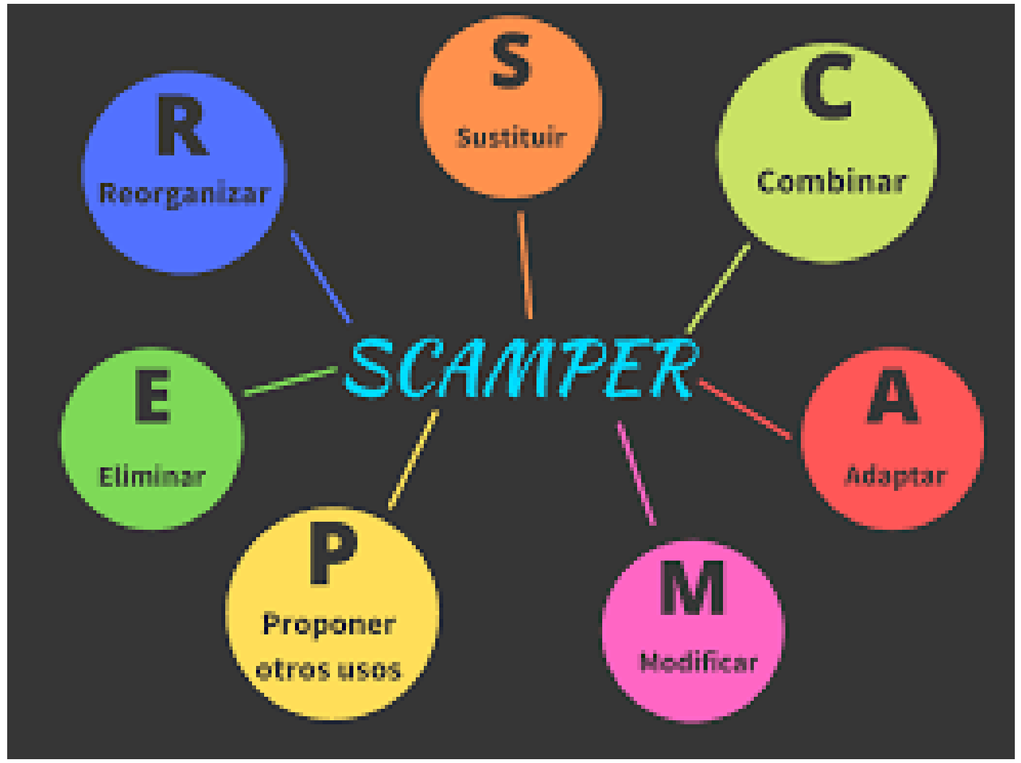

SUSTITUIR

Sustituir la App por una versión web ‘Lite’ para consultar desde cualquier dispositivo sin necesidad de geolocalización o descarga

COMBINAR

Combinar la información de los puestos temporales del Rastro con los locales comerciales permanentes cercanos (locales de moda, tiendas de antigüedad, ...)

ADAPTAR

Adaptar la funcionalidad de voz para crear rutas temáticas guiadas por audio

PONER EN OTRO USO

Usar la tecnología de mapeo y gestión para otros mercados temporales, ferias y eventos dentro y fuera de Madrid

ELIMINAR

Eliminar la complejidad del mapa y GPS en una vista alternativa, ofreciendo solo un simple “Modo Catálogo/Menú” de productos y listados

REORGANIZAR

Reorganizar el mapa para priorizar y destacar zonas de restauración, ocio y tapas cercanas, haciendo la experiencia más social

¿PREGUNTAS?.